VILLA BURI

Contesti simili

In questa presentazione andremo ad elencare tutte quelle realtà che utilizzano la mappatura digitale per monitorare e gestire i loro parchi e spazi verdi. Inoltre, abbiamo deciso di mostrare anche esempi di altri ambienti che utilizzano mappe interattattive per migliorare l'esperienza dei visitatori.

In questo modo, potremo vedere come la tecnologia digitale sta diventando sempre più importante nella gestione sostenibile e innovativa dei parchi e dei territori.

PARCO SEMPIONE

MILANO (ITALIA)

Si estende su una superficie di circa 47 ettari e comprende ampi prati, sentieri per passeggiate e jogging, aree giochi per bambini, giardini botanici e diversi laghetti. Parco Sempione di Milano ha realizzato una mappatura degli alberi del parco, che comprende oltre 5.000 esemplari.

Questa mappatura è stata utilizzata per monitorare la salute degli alberi e per individuare eventuali problemi di gestione.

La mappa è statica e non interrativa e presenta una legenda che indica e vari punti di interesse.

PARCO CAMPIROSSI

REGGIO EMILIA (ITALIA)

È un parco che sorge su una porzione del podere agricolo annesso alla casa in cui visse e lavorò la famiglia Cervi. Presenta una mappa interattiva bidimensionale molto semplificata con le indicazioni della specie floreali presenti.

Ogni numero riporta alla specie della pianta, con un breve descrizione accompagnata da un file audio, in inglese e in italiano.

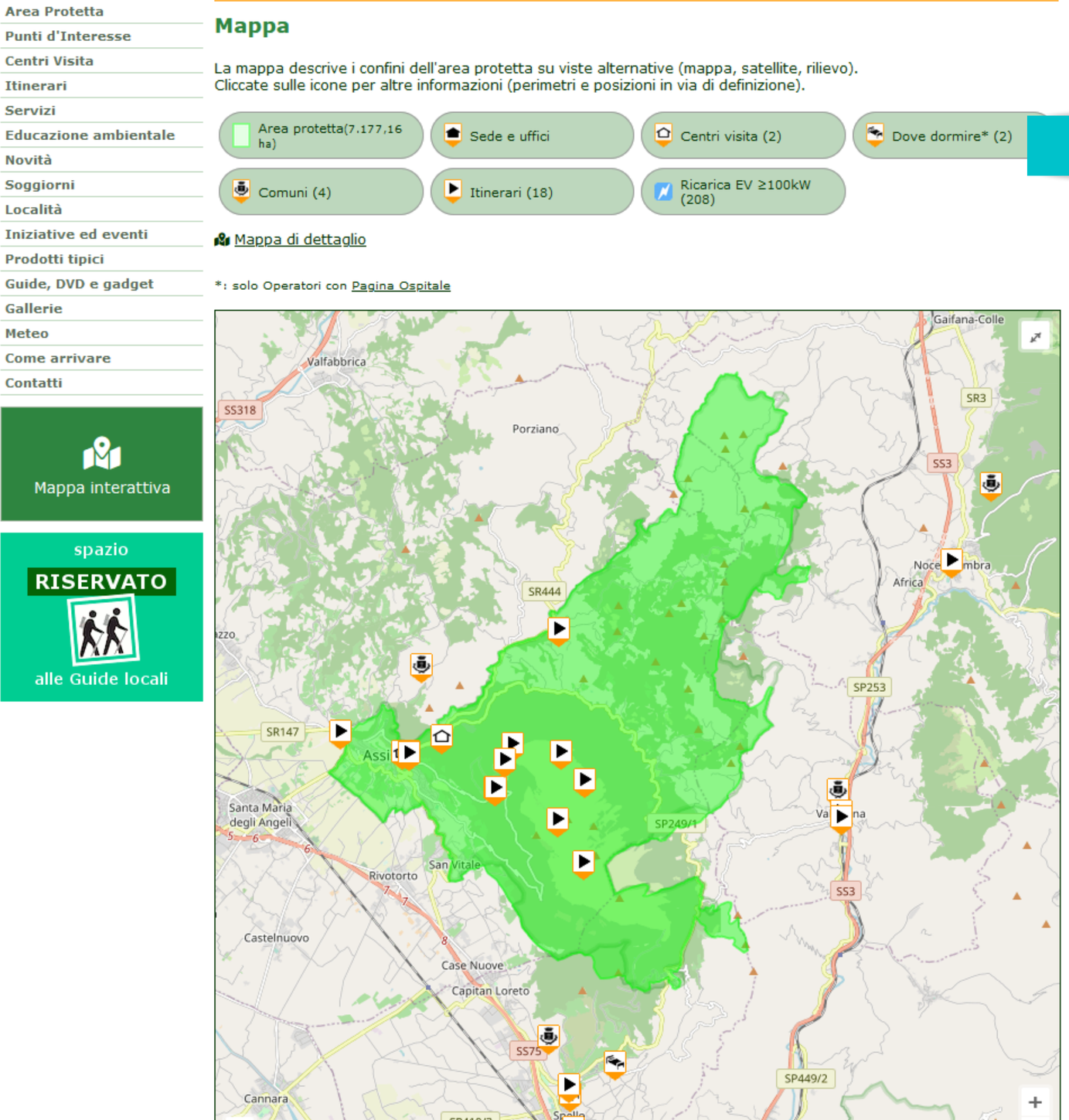

PARCO DEL MONTE SUBASIO

ASSISI (ITALIA)

Il Parco del Monte Subasio ad Assisi ha realizzato una mappatura degli alberi del parco, che comprende circa 6.000 esemplari

La mappa interattiva non è incetrata sulle specie floreali del parco, ma piuttosto sui vari servizi turistici e itinerari e sui comuni presenti nulla zona.

Nel menù a tendina sono presenti anche i punti di interesse, che però vengono solo descritti e non indicati sulla mappa.

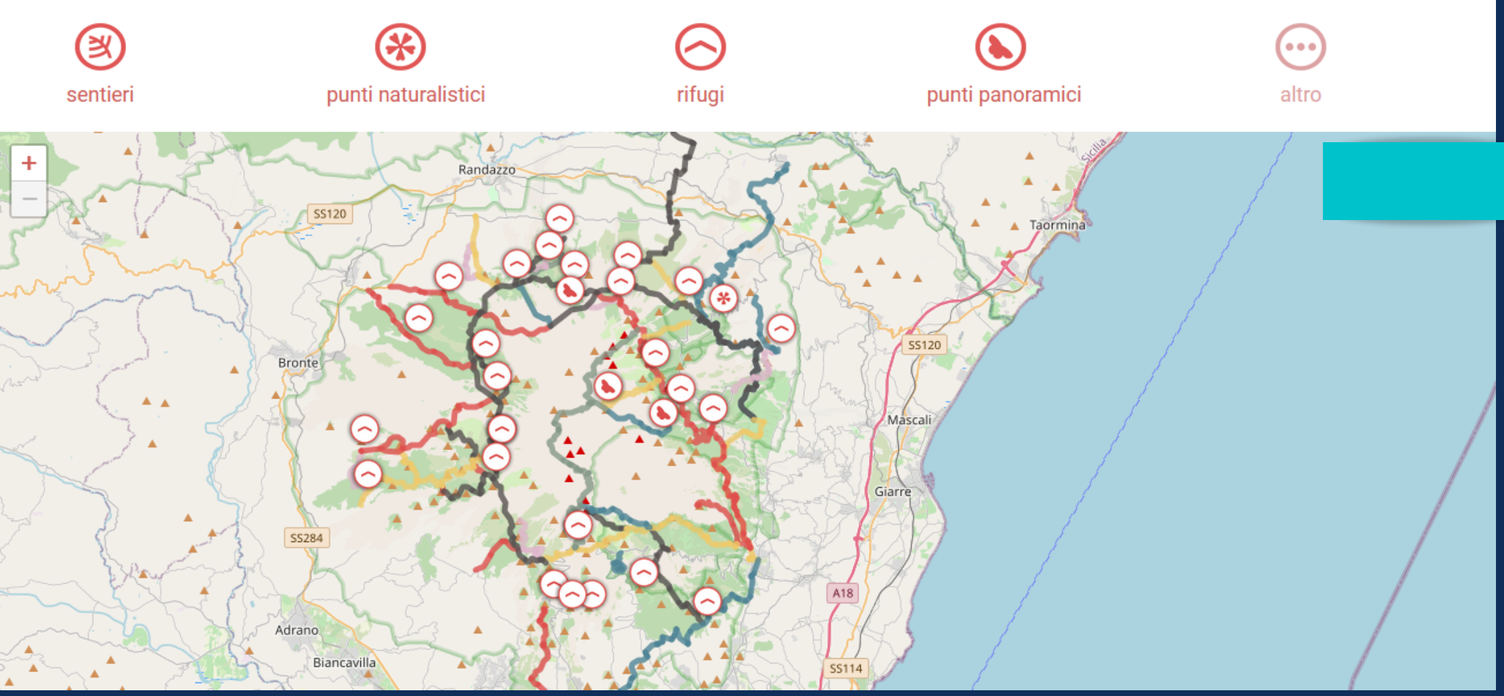

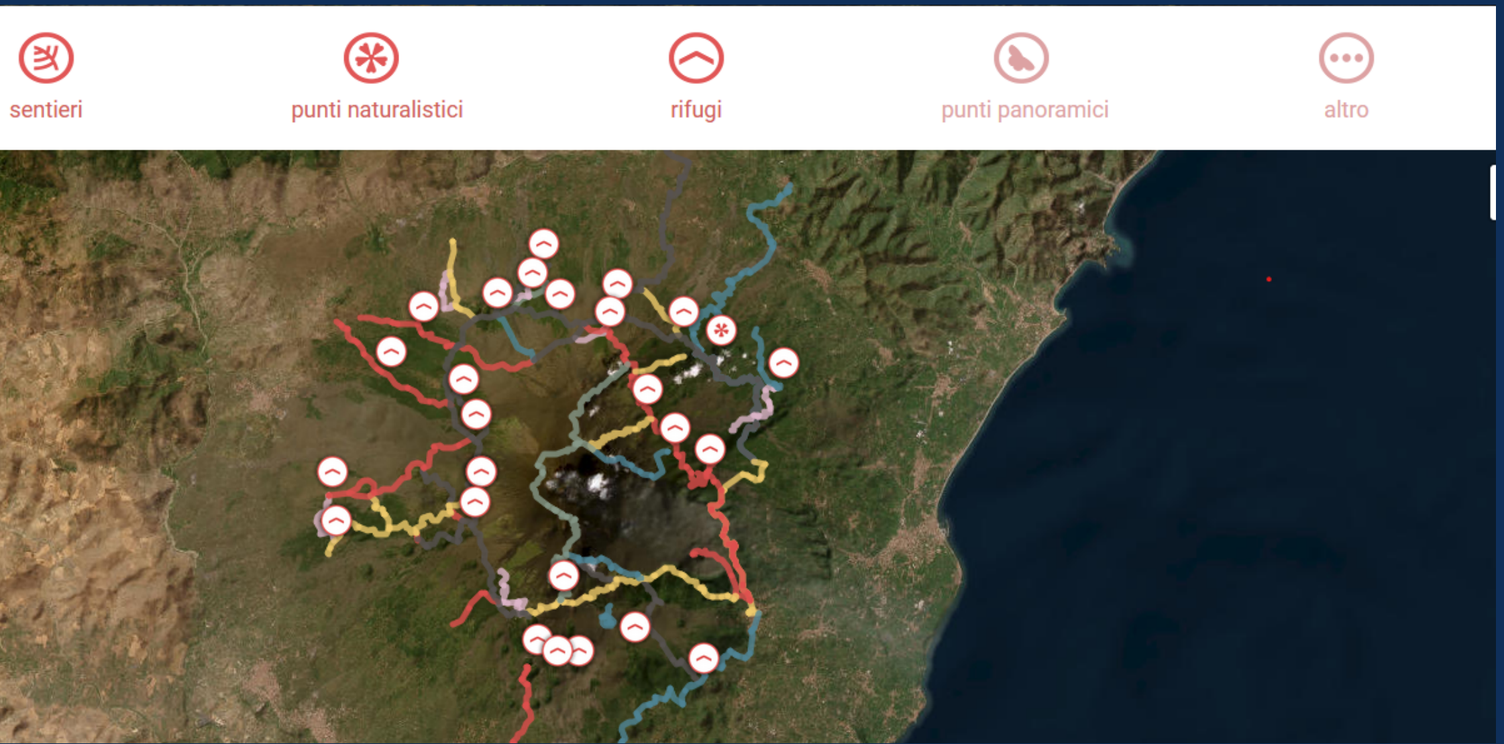

PARCO DELL' ETNA

CATANIA (ITALIA)

Un'area naturale protetta situata in Sicilia che comprende la zona del vulcano Etna, il vulcano attivo più alto d'Europa.

Qui la mappa rivela vari punti di interesse in base alle esigenze dei visitatori. Le destinazioni sono contrassegnate sulla mappa con diversi ‘disegni’, in modo tale da orientare meglio il visitatore. Ogni punto di interesse se selezionato, offre una breve descrizione della zona. Esiste sia una versione geografica che una versione satellitare ed è presente anche un app per smartphone.



EUROPA PARK

RUST (GERMANIA)

Europa Park è un parco divertimenti tedesco e uno dei maggiori in Europa.

Sulla mappa sono indicati i punti di interesse, dove ogni numero è una macroarea del parco che riporta ad una zona specifica. E' integrata molto bene con il sito in quanto consente tramite un menù a tendina sulla sinistra di navigare nelle varie sezioni.

EFTELING PARK

KAATSHEUVEL (PAESI BASSI)

È uno dei parchi divertimento a tema più antichi al mondo.

La mappa riporta quattro macroaree principali, divise principalmente tra attrazioni e hotel. Sono presenti molti filtri riguardo l'entrata per le attrazioni (ad esempio attrazioni adatte a persone alte almeno un metro, attrazioni adatte a persone con disabilità, ecc.) e le zone di ristoro (chiuse o aperte dopo la chiusura del parco, servizio al tavolo, take away, ecc.).